# Etude d’accès à l’eau potable

01/2026

Bastien Leblanc

# 1 – Contexte

L'association DWFA à pour ambition de **donner accès à l'eau au plus grand nombre**.

Un bailleur de fonds à été sollicité avec pour objectif **d'investir dans l'un des 3 domaines d'expertise** de la DWFA :

- Création de services d'accès à l'eau potable
- Modernisation des services déjà existants
- Consulting auprès des administrations

Ce document présente la **construction d'un dashboard**, permettant d'effectuer une **première analyse de ces 3 indicateurs**.

# 2 – Etude du besoin

Cahier des charges du dashboard, convenu lors de la réunion de lancement :

## Mesure de ces indicateurs dans le temps :

- Taux de mortalité dû à de l'eau insalubre
- Population / Densité de la population
- Part d'habitants ayant accès à l'eau potable
- Stabilité politique

## Mesure de ces indicateurs à l'échelle nationale :

- Création de services
- Modernisation des services
- Consulting

## Exigences techniques :

- 3 vues : Mondial / Continental / National
- 4 graphiques différents
- Représentation temporelle et géographique
- Filtres permettant d'isoler les pays instables
- Nuage de point si 2 variables
- 1 agrégation

- Palette de couleur : bleu
- Jointures
- Modèle optimisé
- Accessibilité

# 2 bis – Mockup du projet (basse fidélité)

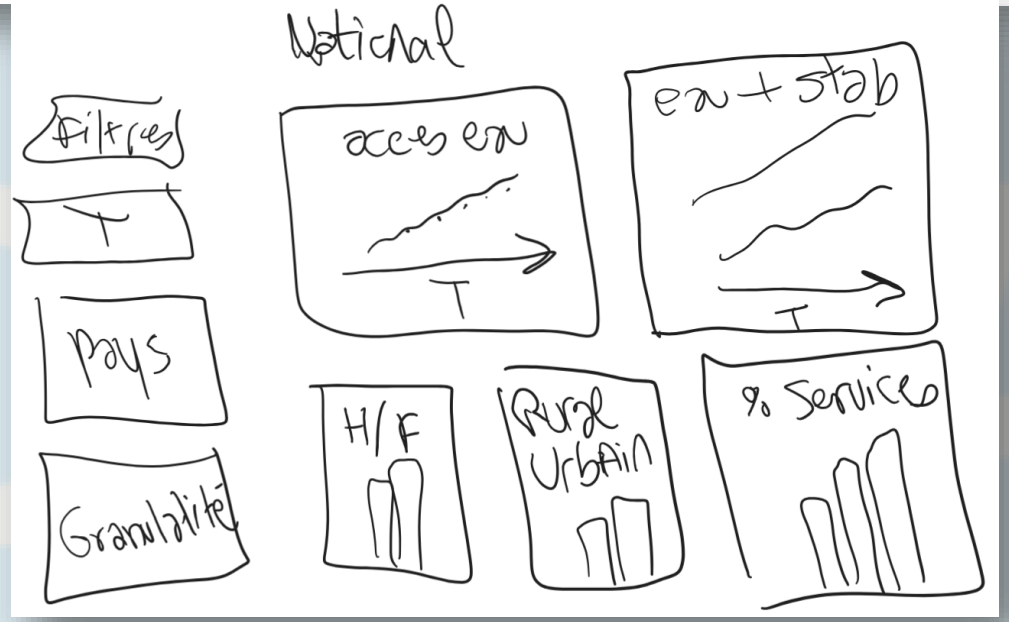

# 3 – Données et logiciel utilisés

5 fichiers CSV représentants :

- Les services d'accès à l'eau
- La mortalité due à une eau insalubre
- La stabilité politique
- La population
- Le référentiel pays/continent (ONG)

Logiciel de datavisualisation :

- Powerbi

PowerBi est pertinent car il permet une modélisation des données et des mesures DAX puissantes et dispose d'une énorme communauté, grâce à son intégration dans l'éco-système Microsoft.

# 4 – Pré-traitement des données

Voici quelques uns des traitements apportés aux données :

- Population[Population] : Multiplication par 1000
- Remplacement des « . » par « , » pour les nombres décimaux
- Configuration du type de données en fonction du contexte (Pourcentage, texte…)

Chaque table contient ces 3 colonnes : *Year / Granularity / Country*, afin de créer un modèle en constellation de faits et créer des relations « 1 à plusieurs », 3 tables de dimensions ont été créés :

- DimYear
- DimGranularity
- DimCountry

DWFA
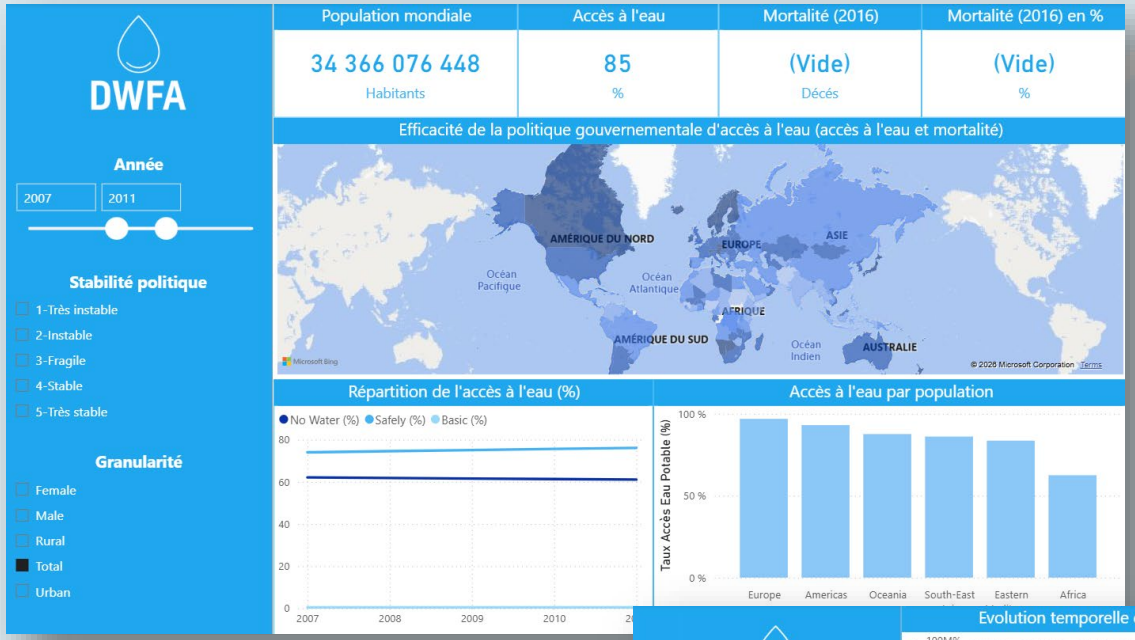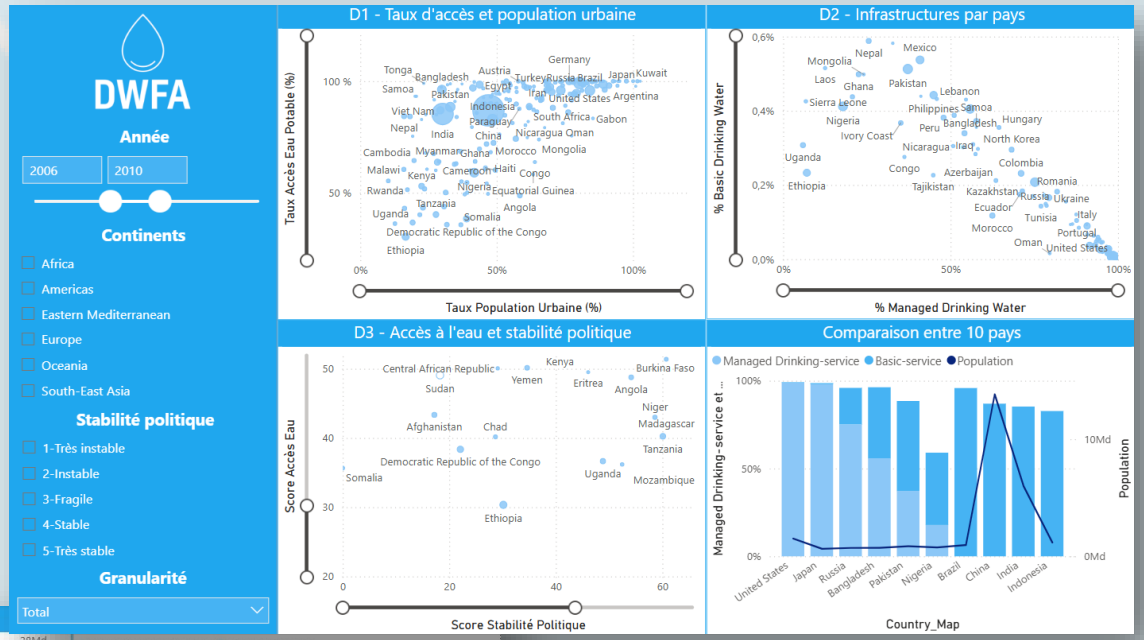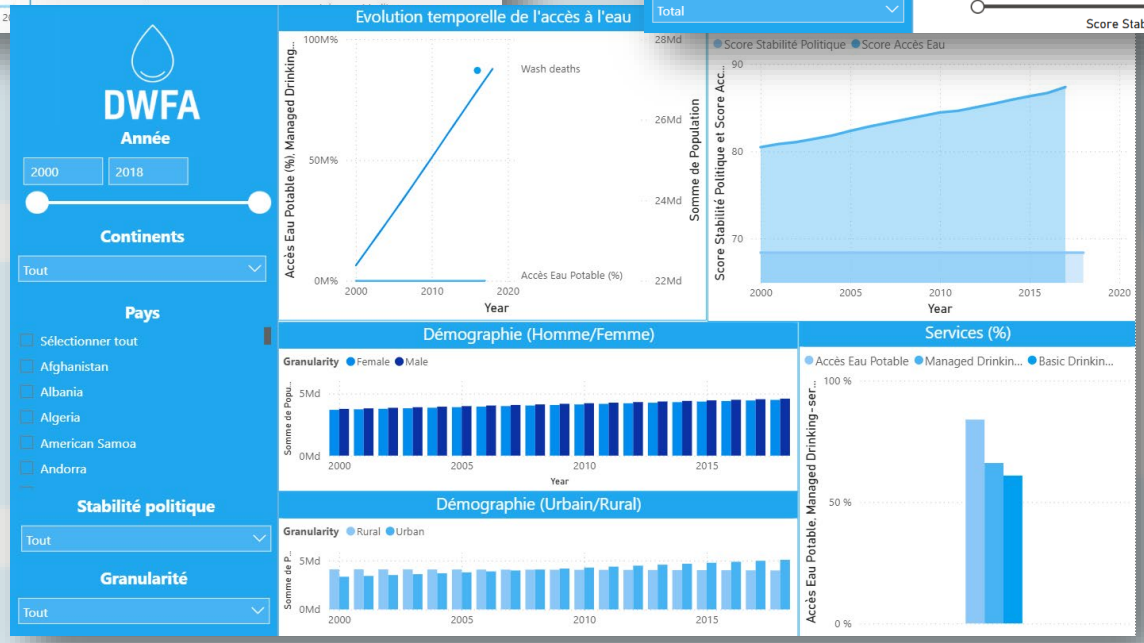
# 6 – Présentation du dashboard